SportsAI

Roni Pursiainen, Simo Vares, Markus Rousu, Nikolas Sederholm
Tietotekniikan tutkinto-ohjelma, ohjelmistokehitys
Mobiilikehitysprojekti 15op
Github-linkki: https://github.com/svares24/Mobiilikehitysprojekti

SportAI

On sovellus, jolla voi mitata omia lenkkejä, ja niitten pituutta, aikaa sekä kestoa. Käyttäjä voi myös tarkastella, poistaa tai uudelleennimetä aikaisempia lenkkejä. Käytimme react-native-gifted-charts kirjastoa diagrammeihin.

Tekoälyvalmentaja

Sovellus sisältää tekoälyllä toimivan valmentajan, jolta voi halutessaan kysyä parannuksia omiin suorituksiin. Tekoäly käy läpi aikaisempia tuloksia ja niiden perusteella antaa uusia suosituksia. Tekoälynä toimii Google Gemini.

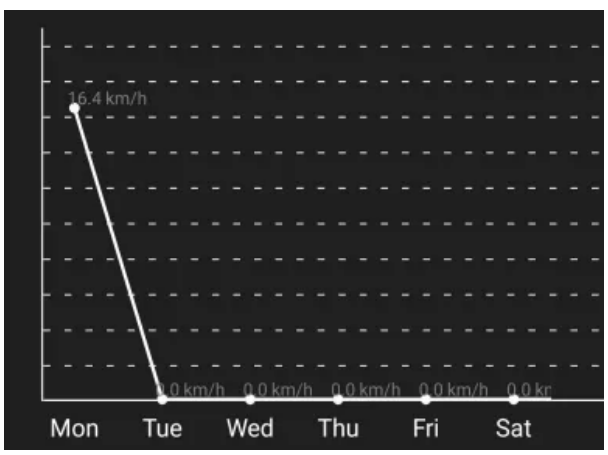

FIGURE 1. Viivadigrammi retkien km/h laskettuna yhteen viikonpäiviltä.

Testaaminen ja Kehitys

Sovellus on tehty käyttämällä Typescript -ohjelmointikieltä ja käyttää React Native. Karttana toimii avoimen lähdekoodina toimiva OpenStreetMap, johon piirretään kuljettu reitti. Kartan reitti tallentuu SQLite tietokantaan, josta haetaan reitin pisteet kun se piirretään uudestaan.

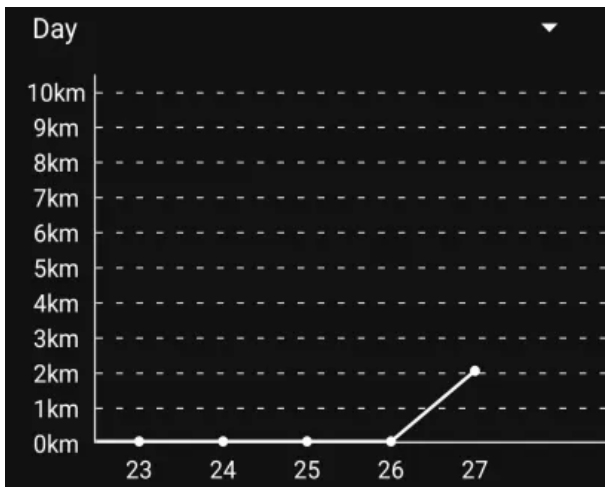

FIGURE 2. Viivadigrammi kilometreistä liikuttu päivässä, kuukaudessa tai vuodessa.

Lopputuotteen arvionti

SportAI auttaa käyttäjää seuraamaan omia lenkkejä ja antaa palautetta parantaakseen tuloksia tai saavuttamaan tavoitteensa. Käyttäjä voi nähdä kuvaajan, jossa näkyy onko suorituksen taso noussut.

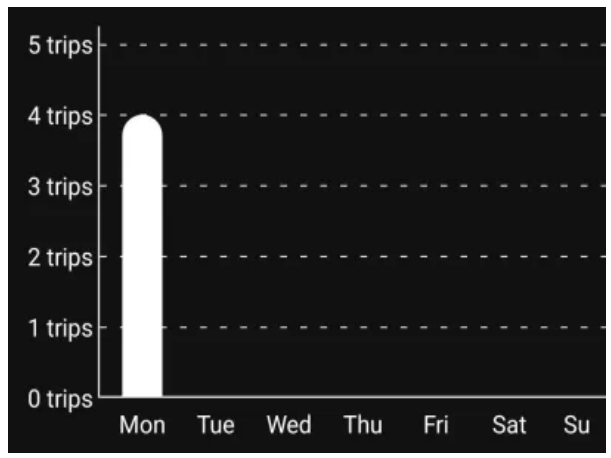

FIGURE 3. Pylväsdigrammi aktiiviteeteista tehty päivässä viimeisen viikon aikana.

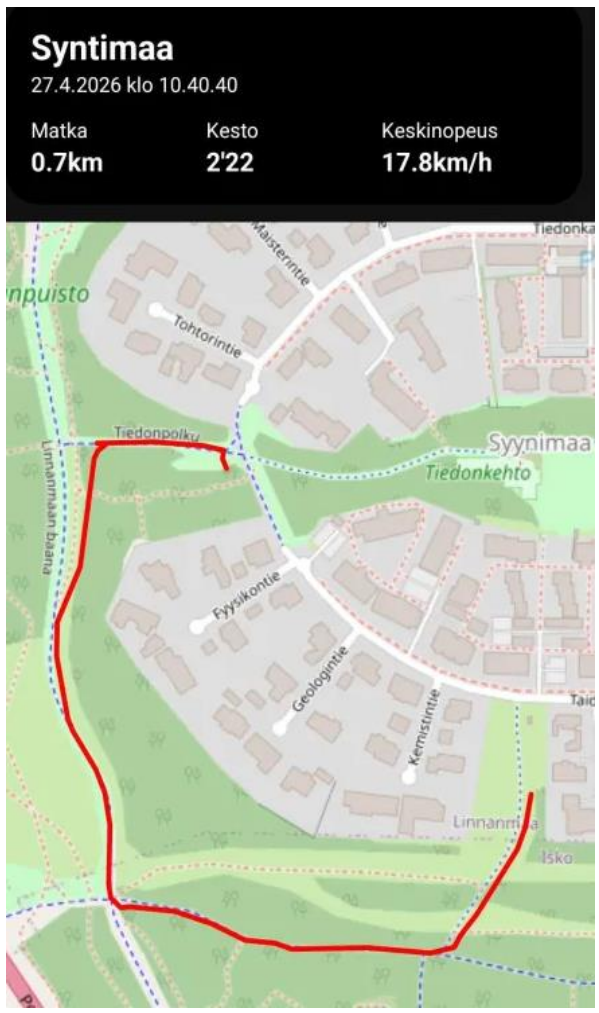

FIGURE 4. Karttanäkymä, kartalle on piirretty reitti murtoviivalla koordinaattipisteiden avulla.

Posterin julkaisupäivä: 27.04.2026
Työryhmä: Ryhmä 17
GitHub repo: https://github.com/svares24/Mobiilikehitysprojekti